EK-11A

Kadastro gören yerlerde yapılacak düzeltme ve değişiklik işlemleri için

TESCİL BİLDİRİMİ

İli	İlçesi	Mahalle veya Köyü	Mevkii
MERSİN	TARSUS	KAYADİBİ	-

~~Düzeltme - Ayırma - Yola Terk - Birleştirme - Cins Değişikliği -~~ İdari Yoldan Tescil

Kütük Sa.No.	Pafta No	Ada No	Parsel No	YÜZÖLÇÜMÜ Ha^2	m^2	dm^2	Cinsi	Maliki	Düşünceler ve İşlemin Şekli
	N33C24D1D	0	A	-	1355	57	HAM TOPRAK	MALİYE HAZİNESİ	İdari Yoldan Tescil. Satış, kiralama vb. işlemler öncesinde Kültür Varlıklarını Koruma Bölge Müdürlüğünden görüş sorulması gerekmektedir. İçme-Kullanma Suyu Havzalarının Korunmasına Dair Yönetmelik 10. Madde hükümlerine uyulması ve taşkına tedbir alınması şartı ile tescilinin yapılmasında DSİ sorumluluk sahası açısındanbir sakınca bulunmamaktadır.

ONAY
Kadastro Müdürü

Fen Kayıt Yıl/No	Düzenleyen Kadastro Müdürlüğü	Kontrol Eden		Fen Klasörüne ve MEGSİS'e		Belediye Encümeni
		Kontrol Memuru	Kontrol Mühendisi	İşlenmiştir	Kontrol edilmiştir	Tarih : No :
Adı Soyadı	Mahmut MELEMEN		Taha GÜRKAN			...../...../20..... Tarih ve ..... Yevmiye Numarası ile tescil edilmiştir.
Tarih						
İmza						

TDA No: 167911

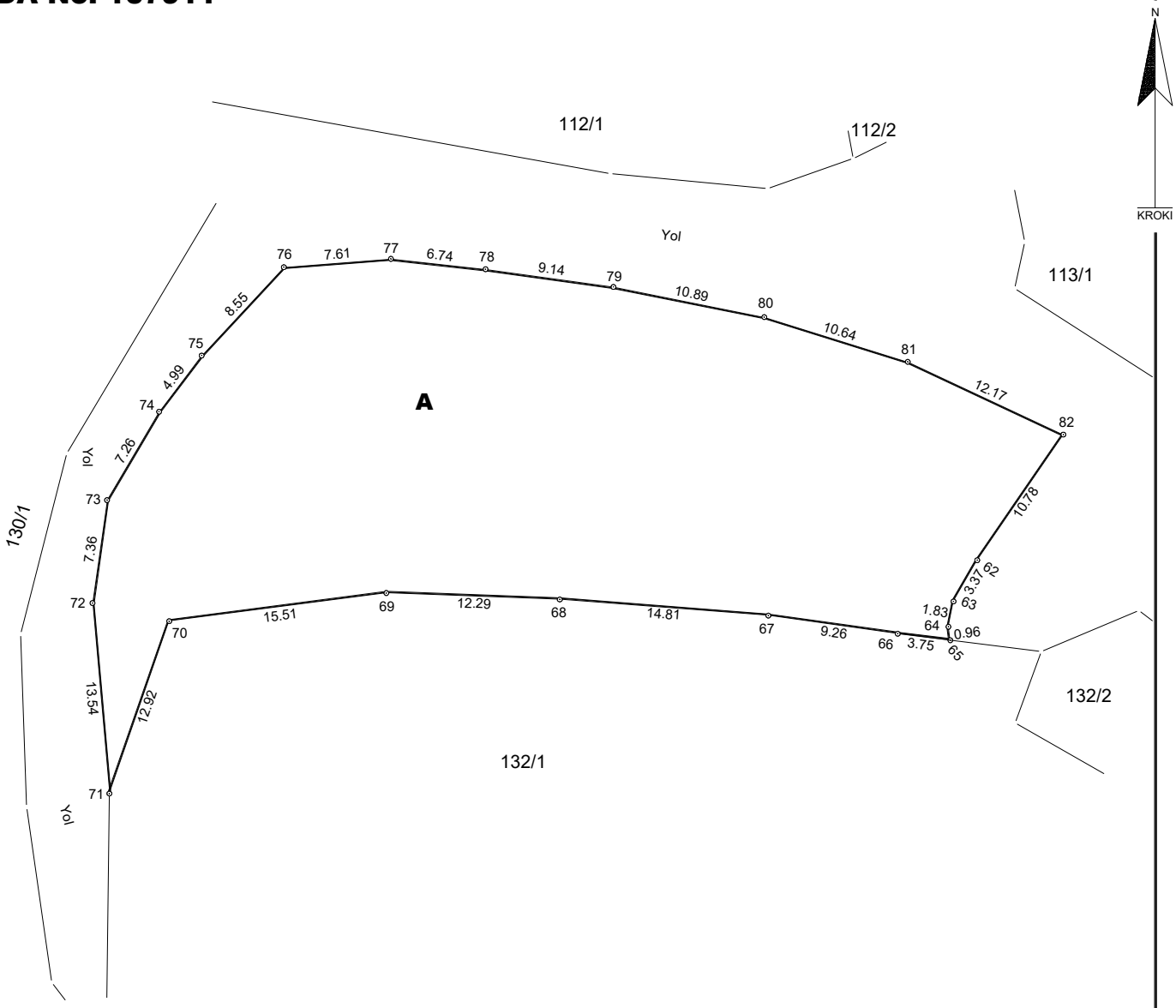

NN	MK	Y	X	NN	MK	Y	X
62	0.09	402547.12	4098635.62	63	0.09	402545.43	4098632.70
64	0.09	402545.08	4098630.90	65		402545.20	4098629.95
66		402541.48	4098630.41	67		402532.32	4098631.69
68		402517.55	4098632.84	69		402505.27	4098633.29
70		402489.89	4098631.30	71		402485.65	4098619.09
72	0.09	402484.46	4098632.58	73	0.09	402485.49	4098639.87
74	0.09	402489.17	4098646.13	75	0.09	402492.19	4098650.11
76	0.09	402498.01	4098656.37	77	0.09	402505.59	4098656.96
78	0.09	402512.29	4098656.22	79	0.09	402521.35	4098654.97
80	0.09	402532.03	4098652.83	81	0.09	402542.19	4098649.67
82	0.09	402553.21	4098644.51				

Ada/Parsel	Noktalar	Hesap Alan
A	62,63,64,65,66,67,68,69,70,71,72,73,74,75,76 77,78,79,80,81,82	1355.57

Elipsoid	GRS80	
Datum	ITRF96	
Başlangıç Epoku	2005.00	
Projeksiyon	UTM (3)	
D.O.M.	36	

Tescil Bildirimi ön sayfasına (EK-11A) uygun düzenlenerek kontrol edilmiştir.

	Düzenleyen Kadastro Müdürlüğü / Lisanslı Büro	Kontrol Eden Kontrol Memuru / Kontrol Mühendisi
Adı Soyadı	Mahmut MELEMEN	Taha GÜRKAN
Tarih		
İmza		

EK-11A

Kadastro gören yerlerde yapılacak düzeltme ve değişiklik işlemleri için

TESCİL BİLDİRİMİ

İli	İlçesi	Mahalle veya Köyü	Mevkii
MERSİN	TARSUS	KAYADİBİ	-

~~Düzeltme - Ayırma - Yola Terk - Birleştirme - Cins Değişikliği -~~ İdari Yoldan Tescil

Kütük Sa.No.	Pafta No	Ada No	Parsel No	YÜZÖLÇÜMÜ Ha^2	m^2	dm^2	Cinsi	Maliki	Düşünceler ve İşlemin Şekli
	N33C24D1D	0	A	-	0294	83	HAM TOPRAK	MALİYE HAZİNESİ	İdari Yoldan Tescil. Satış, kiralama vb. işlemler öncesinde Kültür Varlıklarını Koruma Bölge Müdürlüğünden görüş sorulması gerekmektedir. İçme-Kullanma Suyu Havzalarının Korunmasına Dair Yönetmelik 11. Madde hükümlerine uyulması ve taşkına tedbir alınması şartı ile tescilinin yapılmasında DSİ sorumluluk sahası açısındanbir sakınca bulunmamaktadır.

ONAY
Kadastro Müdürü

Fen Kayıt Yıl/No	Düzenleyen Kadastro Müdürlüğü	Kontrol Eden		Fen Klasörüne ve MEGSİS'e		Belediye Encümeni
		Kontrol Memuru	Kontrol Mühendisi	İşlenmiştir	Kontrol edilmiştir	Tarih : No :
Adı Soyadı	Mahmut MELEMEN		Taha GÜRKAN			...../...../20..... Tarih ve ..... Yevmiye Numarası ile tescil edilmiştir.
Tarih						
İmza						

TDA No: 167912

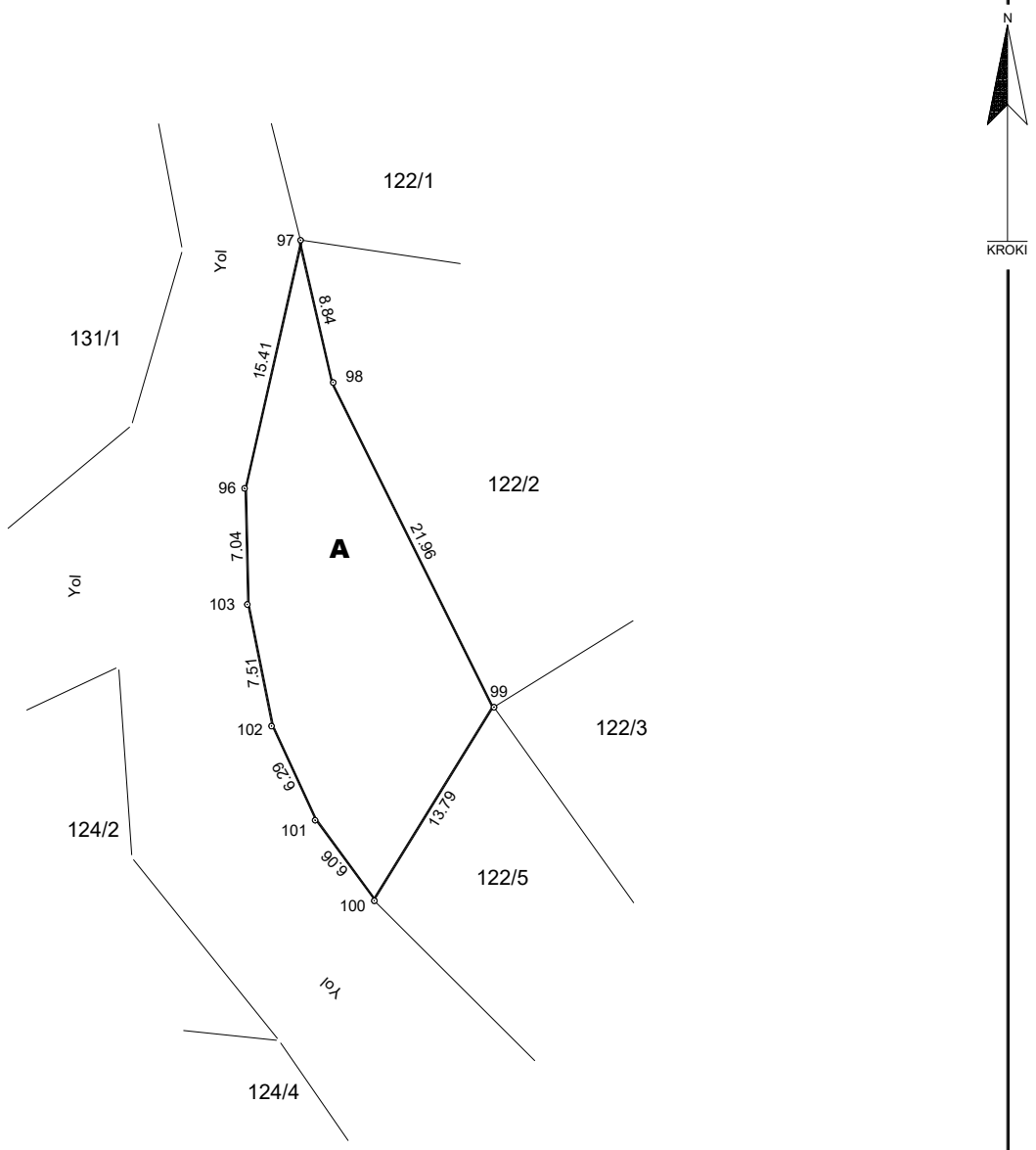

NN	MK	Y	X	NN	MK	Y	X
96	0.09	402535.75	4098530.84	97		402539.14	4098545.87
98		402541.12	4098537.25	99		402550.86	4098517.58
100		402543.61	4098505.85	101	0.09	402540.02	4098510.73
102	0.09	402537.39	4098516.44	103	0.09	402535.91	4098523.80

Ada/Parsel	Noktalar	Hesap Alan
A	96,97,98,99,100,101,102,103	294.83

Elipsoid	GRS80	
Datum	ITRF96	
Başlangıç Epoku	2005.00	
Projeksiyon	UTM (3)	
D.O.M.	36	

Tescil Bildirimi ön sayfasına (EK-11A) uygun düzenlenerek kontrol edilmiştir.

	Düzenleyen Kadastro Müdürlüğü / Lisanslı Büro	Kontrol Eden Kontrol Memuru / Kontrol Mühendisi
Adı Soyadı	Mahmut MELEMEN	Taha GÜRKAN
Tarih		
İmza		

EK-11A

Kadastro gören yerlerde yapılacak düzeltme ve değişiklik işlemleri için

TESCİL BİLDİRİMİ

İli	İlçesi	Mahalle veya Köyü	Mevkii
MERSİN	TARSUS	KAYADİBİ	-

~~Düzeltme - Ayırma - Yola Terk - Birleştirme - Cins Değişikliği -~~ İdari Yoldan Tescil

Kütük Sa.No.	Pafta No	Ada No	Parsel No	YÜZÖLÇÜMÜ Ha^2	m^2	dm^2	Cinsi	Maliki	Düşünceler ve İşlemin Şekli
	N33C24D1D	0	A	-	0350	57	HAM TOPRAK	MALİYE HAZİNESİ	İdari Yoldan Tescil. Satış, kiralama vb. işlemler öncesinde Kültür Varlıklarını Koruma Bölge Müdürlüğünden görüş sorulması gerekmektedir. İçme-Kullanma Suyu Havzalarının Korunmasına Dair Yönetmelik 12. Madde hükümlerine uyulması ve taşkına tedbir alınması şartı ile tescilinin yapılmasında DSİ sorumluluk sahası açısındanbir sakınca bulunmamaktadır.

ONAY
Kadastro Müdürü

Fen Kayıt Yıl/No	Düzenleyen Kadastro Müdürlüğü	Kontrol Eden		Fen Klasörüne ve MEGSİS'e		Belediye Encümeni
		Kontrol Memuru	Kontrol Mühendisi	İşlenmiştir	Kontrol edilmiştir	Tarih : No :
Adı Soyadı	Mahmut MELEMEN		Taha GÜRKAN			...../...../20..... Tarih ve ..... Yevmiye Numarası ile tescil edilmiştir.
Tarih						
İmza						

TDA No: 167913

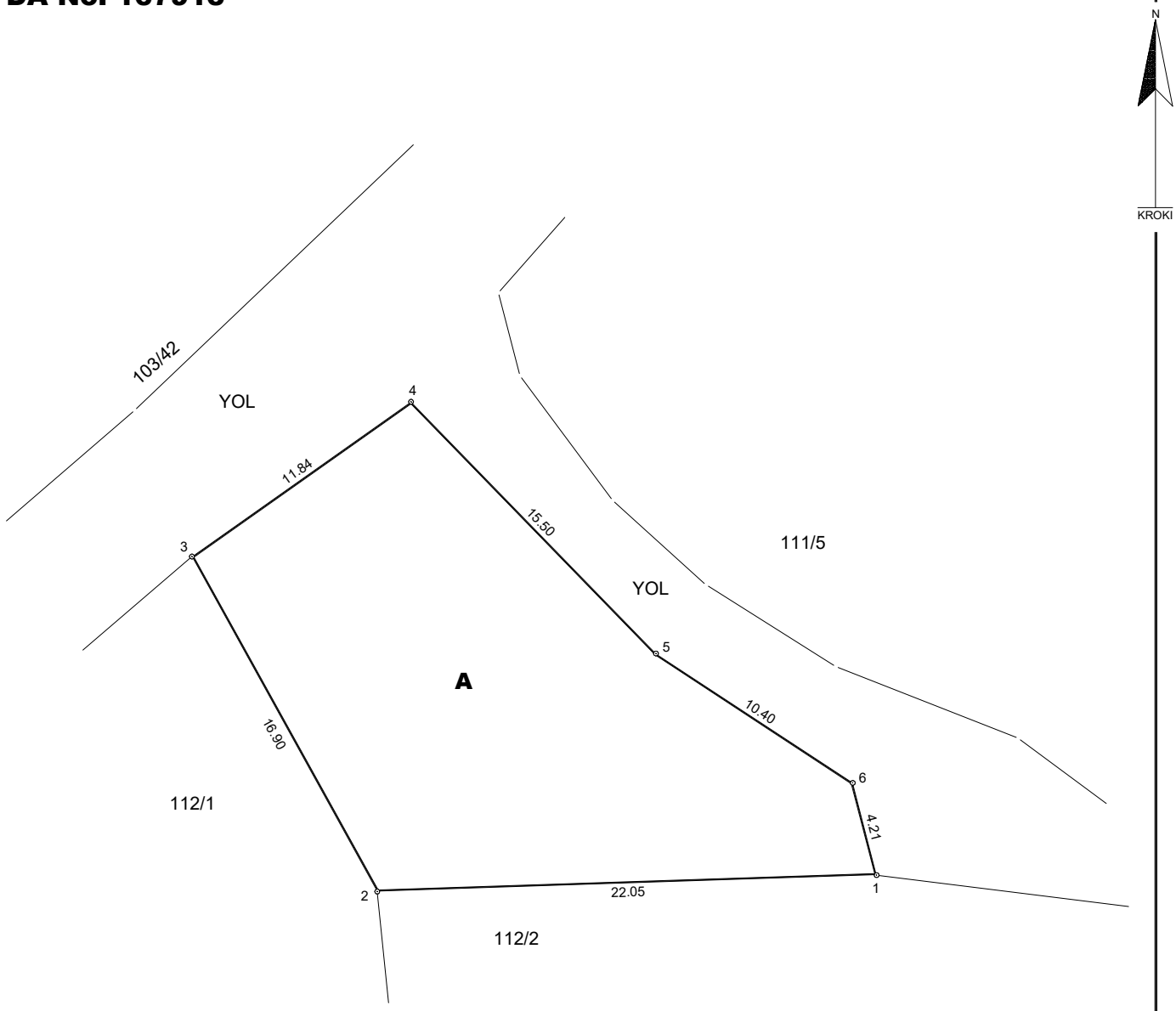

NN	MK	Y	X	NN	MK	Y	X
1		402559.41	4098691.38	2		402537.37	4098690.65
3		402529.19	4098705.44	4	0.09	402538.86	4098712.27
5	0.09	402549.67	4098701.16	6	0.09	402558.36	4098695.45

Ada/Parsel	Noktalar	Hesap Alan
A	1,2,3,4,5,6	350.57

Elipsoid	GRS80	
Datum	ITRF96	
Başlangıç Epoku	2005.00	
Projeksiyon	UTM (3)	
D.O.M.	36	

Tescil Bildirimi ön sayfasına (EK-11A) uygun düzenlenerek kontrol edilmiştir.

	Düzenleyen Kadastro Müdürlüğü / Lisanslı Büro	Kontrol Eden Kontrol Memuru / Kontrol Mühendisi
Adı Soyadı	Mahmut MELEMEN	Taha GÜRKAN
Tarih		
İmza		

EK-11A

Kadastro gören yerlerde yapılacak düzeltme ve değişiklik işlemleri için

TESCİL BİLDİRİMİ

İli	İlçesi	Mahalle veya Köyü	Mevkii
MERSİN	TARSUS	KAYADİBİ	-

~~Düzeltme - Ayırma - Yola Terk - Birleştirme - Cins Değişikliği -~~ İdari Yoldan Tescil

Kütük Sa.No.	Pafta No	Ada No	Parsel No	YÜZÖLÇÜMÜ Ha^2	m^2	dm^2	Cinsi	Maliki	Düşünceler ve İşlemin Şekli
	N33C24D1C	0	A	-	0432	76	HAM TOPRAK	MALİYE HAZİNESİ	İdari Yoldan Tescil. Satış, kiralama vb. işlemler öncesinde Kültür Varlıklarını Koruma Bölge Müdürlüğünden görüş sorulması gerekmektedir. Krokisinde A harfi ile gösterilen yapı bulunmaktadır. İçme-Kullanma Suyu Havzalarının Korunmasına Dair Yönetmelik 12. Madde hükümlerine uyulması ve taşkına tedbir alınması şartı ile tescilinin yapılmasında DSİ sorumluluk sahası açısındanbir sakınca bulunmamaktadır.

ONAY
Kadastro Müdürü

Fen Kayıt Yıl/No	Düzenleyen Kadastro Müdürlüğü	Kontrol Eden		Fen Klasörüne ve MEGSİS'e		Belediye Encümeni
		Kontrol Memuru	Kontrol Mühendisi	İşlenmiştir	Kontrol edilmiştir	Tarih : No :
Adı Soyadı	Mahmut MELEMEN		Taha GÜRKAN			...../...../20..... Tarih ve ..... Yevmiye Numarası ile tescil edilmiştir.
Tarih						
İmza						

TDA No: 224875

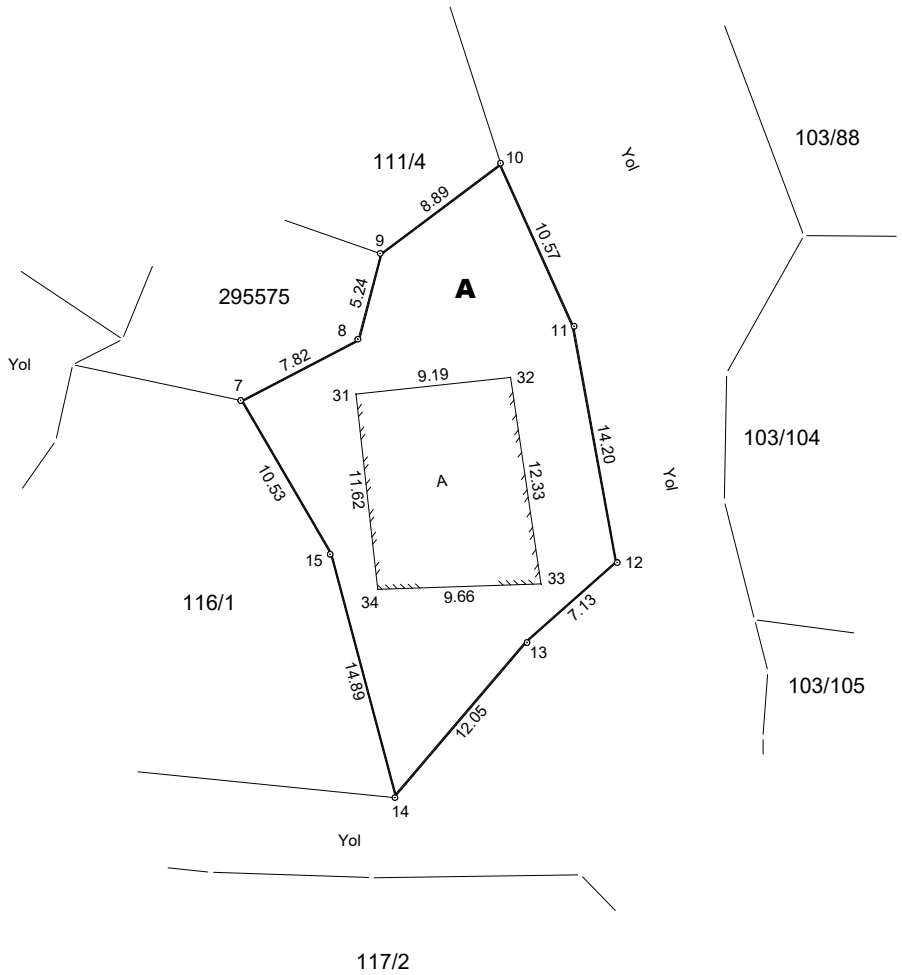

NN	MK	Y	X	NN	MK	Y	X
7		402666.16	4098620.16	8	0.09	402673.10	4098623.79
9		402674.42	4098628.86	10		402681.53	4098634.19
11	0.09	402685.88	4098624.55	12	0.09	402688.43	4098610.58
13	0.09	402683.10	4098605.85	14		402675.29	4098596.68
15		402671.46	4098611.07	31	0.09	402672.99	4098620.54
32	0.09	402682.13	4098621.52	33	0.09	402683.92	4098609.32
34	0.09	402674.27	4098608.99				

Ada/Parsel	Noktalar	Hesap Alan
A	7,8,9,10,11,12,13,14,15	432.76

Elipsoid	GRS80	
Datum	ITRF96	
Başlangıç Epoku	2005.00	
Projeksiyon	UTM (3)	
D.O.M.	36	

Tescil Bildirimi ön sayfasına (EK-11A) uygun düzenlenerek kontrol edilmiştir.

	Düzenleyen Kadastro Müdürlüğü / Lisanslı Büro	Kontrol Eden Kontrol Memuru / Kontrol Mühendisi
Adı Soyadı	Mahmut MELEMEN	Taha GÜRKAN
Tarih		
İmza		

EK-11A

Kadastro gören yerlerde yapılacak düzeltme ve değişiklik işlemleri için

TESCİL BİLDİRİMİ

İli	İlçesi	Mahalle veya Köyü	Mevkii
MERSİN	TARSUS	KAYADİBİ	-

~~Düzeltme - Ayırma - Yola Terk - Birleştirme - Cins Değişikliği -~~ İdari Yoldan Tescil

Kütük Sa.No.	Pafta No	Ada No	Parsel No	YÜZÖLÇÜMÜ Ha^2	m^2	dm^2	Cinsi	Maliki	Düşünceler ve İşlemin Şekli
	N33C24D1C	0	A	-	0114	06	HAM TOPRAK	MALİYE HAZİNESİ	İdari Yoldan Tescil. Satış, kiralama vb. işlemler öncesinde Kültür Varlıklarını Koruma Bölge Müdürlüğünden görüş sorulması gerekmektedir. Krokisinde A harfi ile gösterilen yapı bulunmaktadır. İçme-Kullanma Suyu Havzalarının Korunmasına Dair Yönetmelik 10. Madde hükümlerine uyulması ve taşkına tedbir alınması şartı ile tescilinin yapılmasında DSİ sorumluluk sahası açısındanbir sakınca bulunmamaktadır.

ONAY
Kadastro Müdürü

Fen Kayıt Yıl/No	Düzenleyen Kadastro Müdürlüğü	Kontrol Eden		Fen Klasörüne ve MEGSİS'e		Belediye Encümeni
		Kontrol Memuru	Kontrol Mühendisi	İşlenmiştir	Kontrol edilmiştir	Tarih : No :
Adı Soyadı	Mahmut MELEMEN		Taha GÜRKAN			...../...../20..... Tarih ve ..... Yevmiye Numarası ile tescil edilmiştir.
Tarih						
İmza						

TDA No: 224941

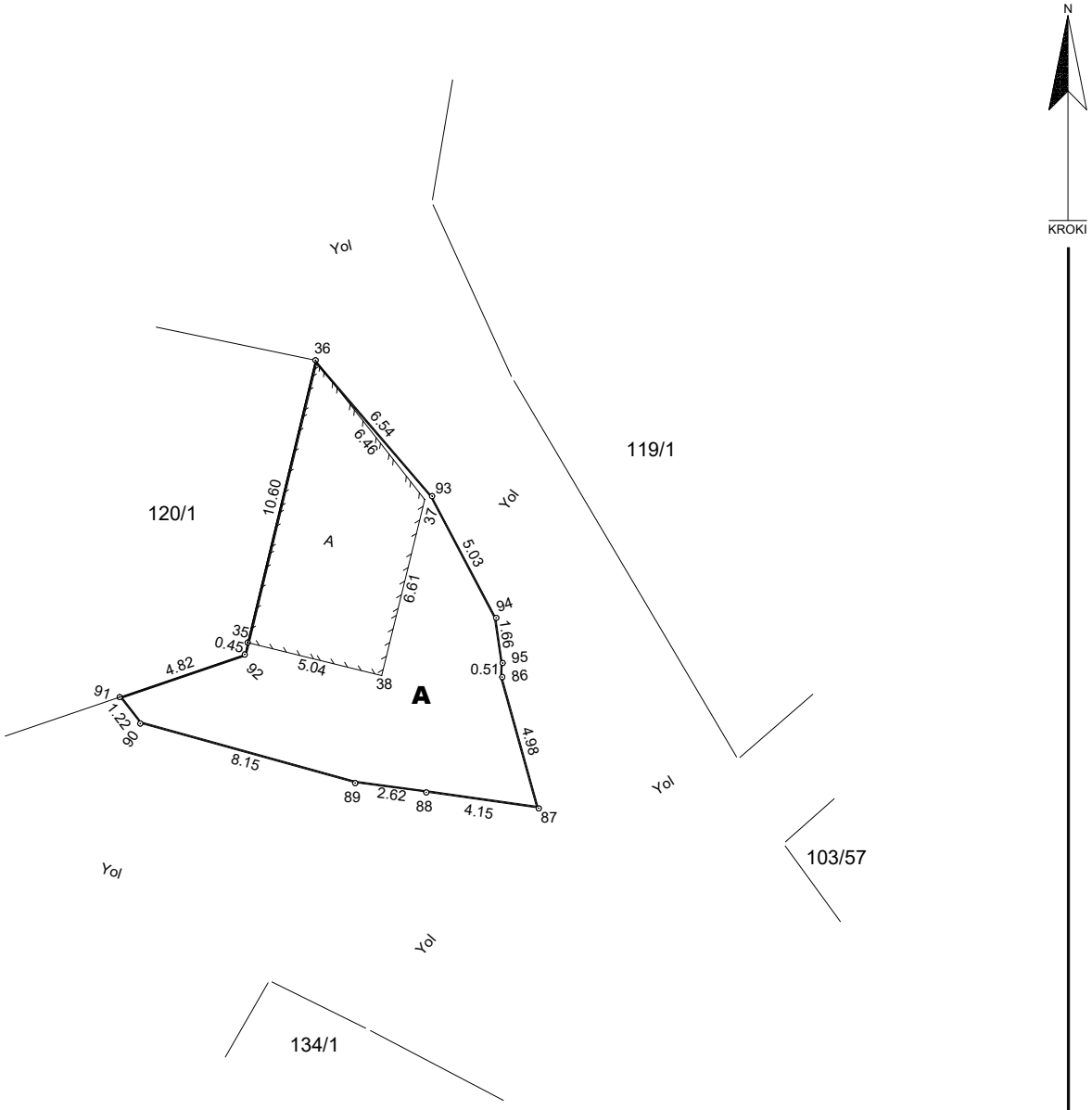

NN	MK	Y	X	NN	MK	Y	X
35	0.09	402703.49	4098499.75	36	0.09	402705.97	4098510.05
37	0.09	402709.96	4098504.97	38	0.09	402708.39	4098498.55
86	0.09	402712.79	4098498.49	87	0.09	402714.13	4098493.69
88	0.09	402710.02	4098494.28	89	0.09	402707.42	4098494.62
90	0.09	402699.57	4098496.79	91		402698.82	4098497.76
92		402703.39	4098499.31	93	0.09	402710.23	4098505.10
94	0.09	402712.57	4098500.65	95	0.09	402712.81	4098499.00

Ada/Parsel	Noktalar	Hesap Alan
A	86,87,88,89,90,91,92,93,94,95	114.06

Elipsoid	GRS80	
Datum	ITRF96	
Başlangıç Epoku	2005.00	
Projeksiyon	UTM (3)	
D.O.M.	36	

Tescil Bildirimi ön sayfasına (EK-11A) uygun düzenlenerek kontrol edilmiştir.

	Düzenleyen Kadastro Müdürlüğü / Lisanslı Büro	Kontrol Eden Kontrol Memuru / Kontrol Mühendisi
Adı Soyadı	Mahmut MELEMEN	Taha GÜRKAN
Tarih		
İmza		

EK-11A

Kadastro gören yerlerde yapılacak düzeltme ve değişiklik işlemleri için

TESCİL BİLDİRİMİ

İli	İlçesi	Mahalle veya Köyü	Mevkii
MERSİN	TARSUS	KAYADİBİ	-

~~Düzeltme - Ayırma - Yola Terk - Birleştirme - Cins Değişikliği -~~ İdari Yoldan Tescil

Kütük Sa.No.	Pafta No	Ada No	Parsel No	YÜZÖLÇÜMÜ Ha^2	m^2	dm^2	Cinsi	Maliki	Düşünceler ve İşlemin Şekli
	N33C24D1D	0	A	-	0175	34	HAM TOPRAK	MALİYE HAZİNESİ	İdari Yoldan Tescil. Satış, kiralama vb. işlemler öncesinde Kültür Varlıklarını Koruma Bölge Müdürlüğünden görüş sorulması gerekmektedir. Krokide A ile gösterilen 111/5 no'lu parselde ki yapının işbu parsele 18.20 m2 taşkın kullanımı bulunmaktadır. İçme-Kullanma Suyu Havzalarının Korunmasına Dair Yönetmelik 10. Madde hükümlerine uyulması ve taşkına tedbir alınması şartı ile tescilinin yapılmasında DSİ sorumluluk sahası açısındanbir sakınca bulunmamaktadır.

ONAY
Kadastro Müdürü

Fen Kayıt Yıl/No	Düzenleyen Kadastro Müdürlüğü	Kontrol Eden		Fen Klasörüne ve MEGSİS'e		Belediye Encümeni
		Kontrol Memuru	Kontrol Mühendisi	İşlenmiştir	Kontrol edilmiştir	Tarih : No :
Adı Soyadı	Mahmut MELEMEN		Taha GÜRKAN			...../...../20..... Tarih ve ..... Yevmiye Numarası ile tescil edilmiştir.
Tarih						
İmza						

TDA No: 225010

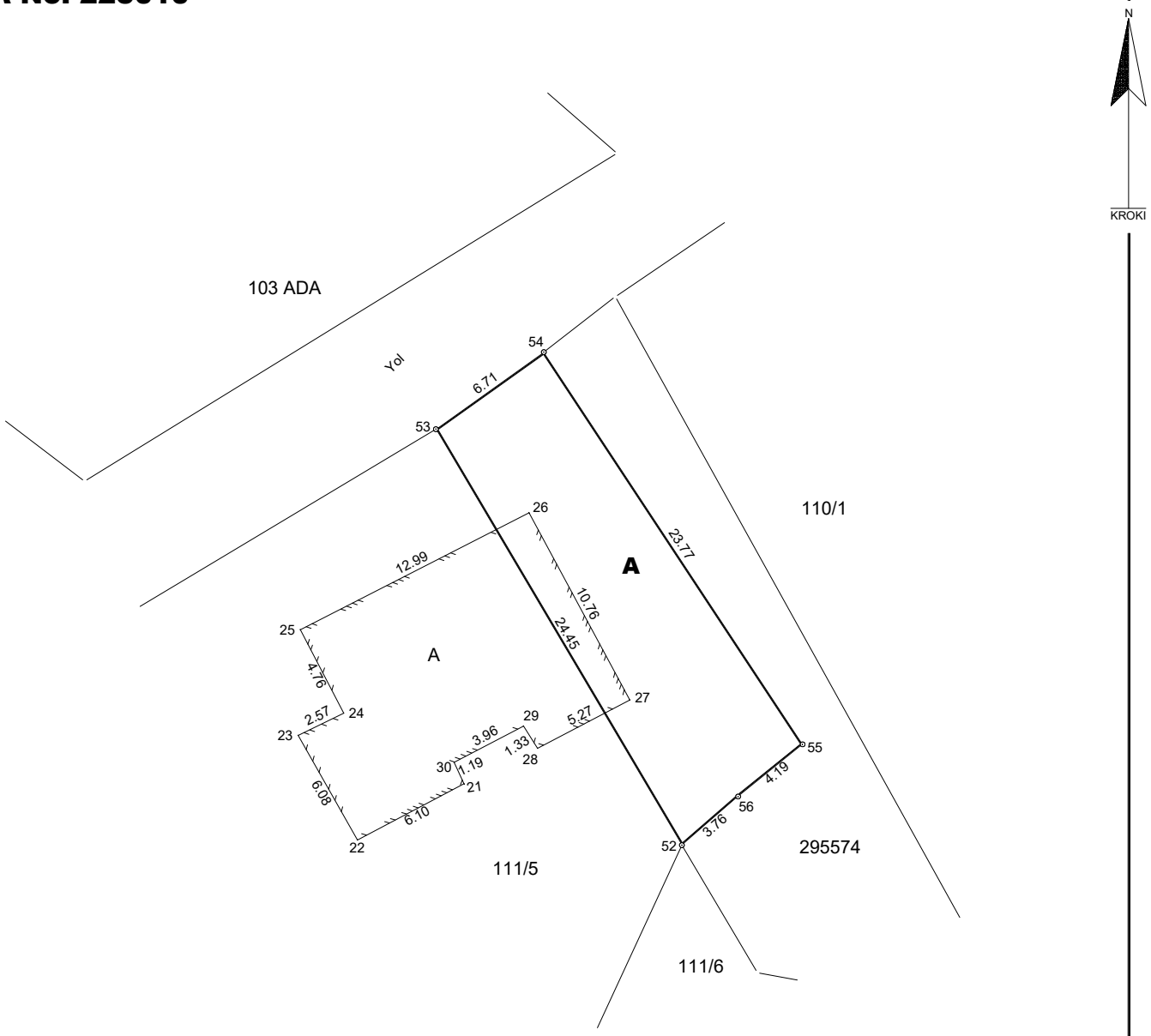

NN	MK	Y	X	NN	MK	Y	X
21	0.09	402573.42	4098725.71	22	0.09	402568.02	4098722.86
23	0.09	402565.03	4098728.14	24	0.09	402567.34	4098729.27
25	0.09	402565.14	4098733.50	26	0.09	402576.71	4098739.41
27	0.09	402581.81	4098729.94	28	0.09	402577.14	4098727.50
29	0.09	402576.43	4098728.62	30	0.09	402572.91	4098726.79
52		402584.44	4098722.60	53		402572.00	4098743.64
54	0.09	402577.46	4098747.54	55	0.09	402590.54	4098727.70
56	0.09	402587.29	4098725.06				

Ada/Parsel	Noktalar	Hesap Alan
A	52,53,54,55,56	175.34

Elipsoid	GRS80	
Datum	ITRF96	
Başlangıç Epoku	2005.00	
Projeksiyon	UTM (3)	
D.O.M.	36	

Tescil Bildirimi ön sayfasına (EK-11A) uygun düzenlenerek kontrol edilmiştir.

	Düzenleyen Kadastro Müdürlüğü / Lisanslı Büro	Kontrol Eden Kontrol Memuru / Kontrol Mühendisi
Adı Soyadı	Mahmut MELEMEN	Taha GÜRKAN
Tarih		
İmza		

EK-11A

Kadastro gören yerlerde yapılacak düzeltme ve değişiklik işlemleri için

TESCİL BİLDİRİMİ

İli	İlçesi	Mahalle veya Köyü	Mevkii
MERSİN	TARSUS	KAYADİBİ	-

~~Düzeltme - Ayırma - Yola Terk - Birleştirme - Cins Değişikliği -~~ İdari Yoldan Tescil

Kütük Sa.No.	Pafta No	Ada No	Parsel No	YÜZÖLÇÜMÜ Ha^2	m^2	dm^2	Cinsi	Maliki	Düşünceler ve İşlemin Şekli
	N33C24D1C	0	A	-	0345	58	HAM TOPRAK	MALİYE HAZİNESİ	İdari Yoldan Tescil. Satış, kiralama vb. işlemler öncesinde Kültür Varlıklarını Koruma Bölge Müdürlüğünden görüş sorulması gerekmektedir. İçme-Kullanma Suyu Havzalarının Korunmasına Dair Yönetmelik 10. Madde hükümlerine uyulması ve taşkına tedbir alınması şartı ile tescilinin yapılmasında DSİ sorumluluk sahası açısındanbir sakınca bulunmamaktadır.

ONAY
Kadastro Müdürü

Fen Kayıt Yıl/No	Düzenleyen Kadastro Müdürlüğü	Kontrol Eden		Fen Klasörüne ve MEGSİS'e		Belediye Encümeni
		Kontrol Memuru	Kontrol Mühendisi	İşlenmiştir	Kontrol edilmiştir	Tarih : No :
Adı Soyadı	Mahmut MELEMEN		Taha GÜRKAN			...../...../20..... Tarih ve ..... Yevmiye Numarası ile tescil edilmiştir.
Tarih						
İmza						

TDA No: 225011

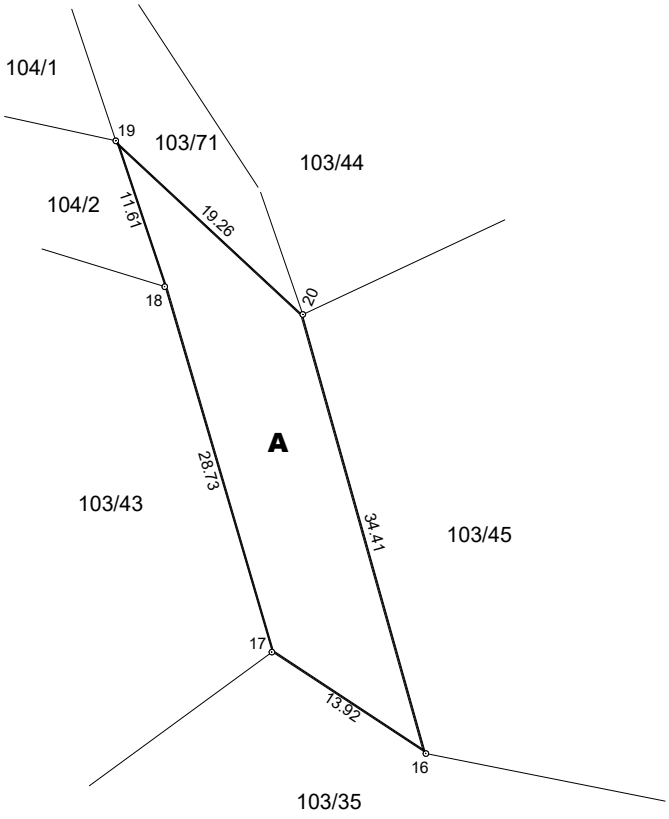

NN	MK	Y	X	NN	MK	Y	X
16		402667.06	4098916.26	17		402655.44	4098923.92
18		402647.35	4098951.49	19		402643.66	4098962.50
20		402657.77	4098949.40				

Ada/Parsel	Noktalar	Hesap Alan
A	16,17,18,19,20	345.58

Elipsoid	GRS80	
Datum	ITRF96	
Başlangıç Epoku	2005.00	
Projeksiyon	UTM (3)	
D.O.M.	36	

Tescil Bildirimi ön sayfasına (EK-11A) uygun düzenlenerek kontrol edilmiştir.

	Düzenleyen Kadastro Müdürlüğü / Lisanslı Büro	Kontrol Eden Kontrol Memuru / Kontrol Mühendisi
Adı Soyadı	Mahmut MELEMEN	Taha GÜRKAN
Tarih		
İmza		

EK-11A

Kadastro gören yerlerde yapılacak düzeltme ve değişiklik işlemleri için

TESCİL BİLDİRİMİ

İli	İlçesi	Mahalle veya Köyü	Mevkii
MERSİN	TARSUS	KAYADİBİ	-

~~Düzeltme - Ayırma - Yola Terk - Birleştirme - Cins Değişikliği -~~ İdari Yoldan Tescil

Kütük Sa.No.	Pafta No	Ada No	Parsel No	YÜZÖLÇÜMÜ Ha	m^2	dm^2	Cinsi	Maliki	Düşünceler ve İşlemin Şekli
	N33C24D4A	0	A	-	0235	10	HAM TOPRAK	MALİYE HAZİNESİ	İdari Yoldan Tescil. Satış, kiralama vb. işlemler öncesinde Kültür Varlıklarını Koruma Bölge Müdürlüğünden görüş sorulması gerekmektedir. Krokisinde A harfi ile gösterilen yapı bulunmaktadır. İçme-Kullanma Suyu Havzalarının Korunmasına Dair Yönetmelik 10. Madde hükümlerine uyulması ve taşkına tedbir alınması şartı ile tescilinin yapılmasında DSİ sorumluluk sahası açısındanbir sakınca bulunmamaktadır.

ONAY
Kadastro Müdürü

Fen Kayıt Yıl/No	Düzenleyen Kadastro Müdürlüğü	Kontrol Eden		Fen Klasörüne ve MEGSİS'e		Belediye Encümeni
		Kontrol Memuru	Kontrol Mühendisi	İşlenmiştir	Kontrol edilmiştir	Tarih : No :
Adı Soyadı	Mahmut MELEMEN		Taha GÜRKAN			...../...../20..... Tarih ve ..... Yevmiye Numarası ile tescil edilmiştir.
Tarih						
İmza						

TDA No: 225124

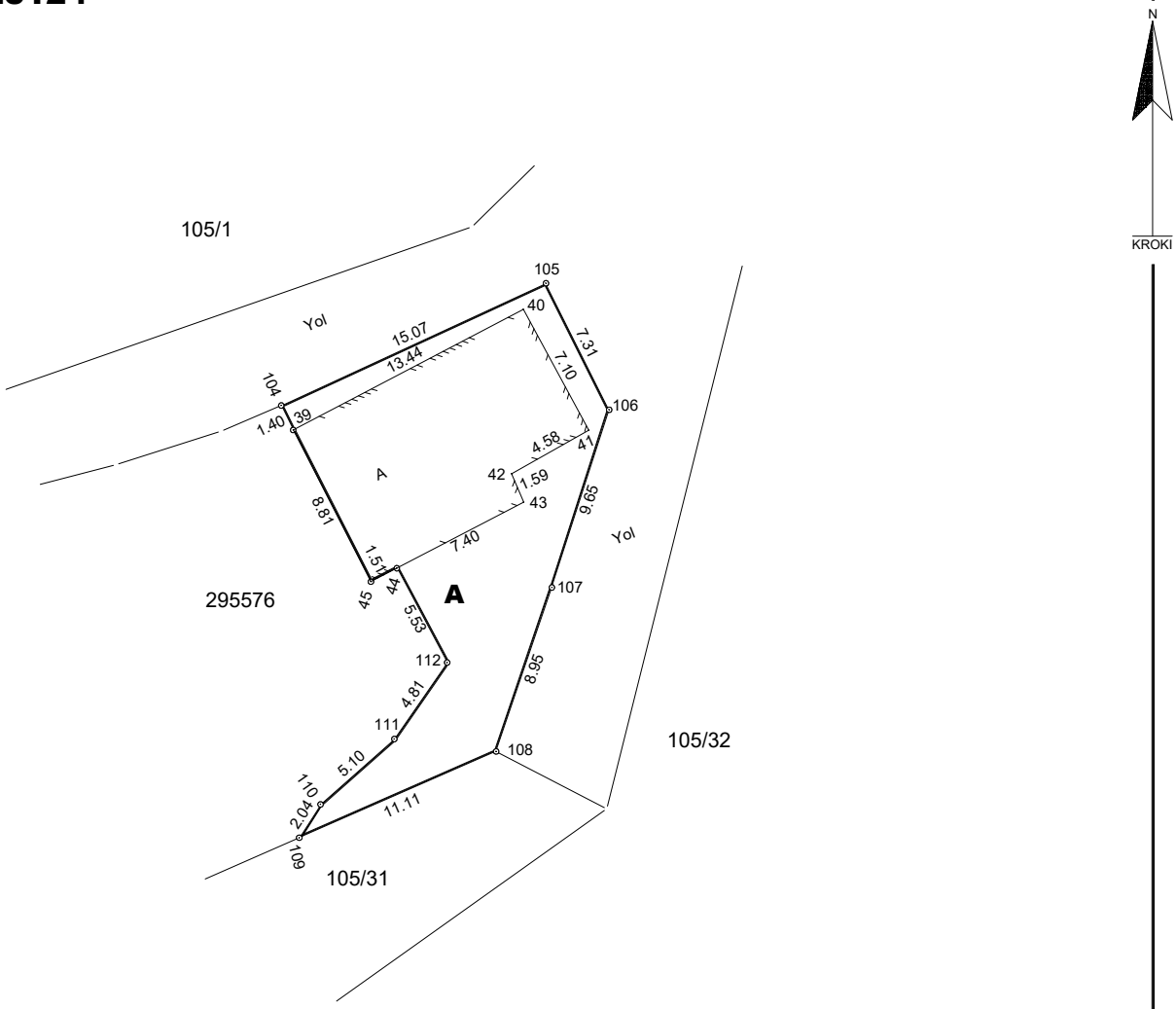

NN	MK	Y	X	NN	MK	Y	X
39	0.09	402224.20	4098333.41	40	0.09	402236.10	4098339.65
41	0.09	402239.48	4098333.41	42	0.09	402235.49	4098331.14
43	0.09	402236.13	4098329.69	44	0.09	402229.56	4098326.27
45	0.09	402228.22	4098325.57	104	0.09	402223.58	4098334.68
105	0.09	402237.27	4098340.99	106	0.09	402240.54	4098334.46
107	0.09	402237.58	4098325.27	108		402234.69	4098316.80
109		402224.51	4098312.34	110	0.09	402225.61	4098314.06
111	0.09	402229.43	4098317.44	112	0.09	402232.16	4098321.40

Ada/Parsel	Noktalar	Hesap Alan
A	104,105,106,107,108,109,110,111,112	235.10

Elipsoid	GRS80	
Datum	ITRF96	
Başlangıç Epoku	2005.00	
Projeksiyon	UTM (3)	
D.O.M.	36	

Tescil Bildirimi ön sayfasına (EK-11A) uygun düzenlenerek kontrol edilmiştir.

	Düzenleyen Kadastro Müdürlüğü / Lisanslı Büro	Kontrol Eden Kontrol Memuru / Kontrol Mühendisi
Adı Soyadı	Mahmut MELEMEN	Taha GÜRKAN
Tarih		
İmza		

EK-11A

Kadastro gören yerlerde yapılacak düzeltme ve değişiklik işlemleri için

TESCİL BİLDİRİMİ

İli	İlçesi	Mahalle veya Köyü	Mevkii
MERSİN	TARSUS	KAYADİBİ	-

~~Düzeltme - Ayırma - Yola Terk - Birleştirme - Cins Değişikliği -~~ İdari Yoldan Tescil

Kütük Sa.No.	Pafta No	Ada No	Parsel No	YÜZÖLÇÜMÜ Ha^2	m^2	dm^2	Cinsi	Maliki	Düşünceler ve İşlemin Şekli
	N33C24D1D	0	A	-	0216	48	HAM TOPRAK	MALİYE HAZİNESİ	İdari Yoldan Tescil. Satış, kiralama vb. işlemler öncesinde Kültür Varlıklarını Koruma Bölge Müdürlüğünden görüş sorulması gerekmektedir. İçme-Kullanma Suyu Havzalarının Korunmasına Dair Yönetmelik 10. Madde hükümlerine uyulması ve taşkına tedbir alınması şartı ile tescilinin yapılmasında DSİ sorumluluk sahası açısındanbir sakınca bulunmamaktadır.

ONAY
Kadastro Müdürü

Fen Kayıt Yıl/No	Düzenleyen Kadastro Müdürlüğü	Kontrol Eden		Fen Klasörüne ve MEGSİS'e		Belediye Encümeni
		Kontrol Memuru	Kontrol Mühendisi	İşlenmiştir	Kontrol edilmiştir	Tarih : No :
Adı Soyadı	Mahmut MELEMEN		Taha GÜRKAN			...../...../20..... Tarih ve ..... Yevmiye Numarası ile tescil edilmiştir.
Tarih						
İmza						

TDA No: 295574

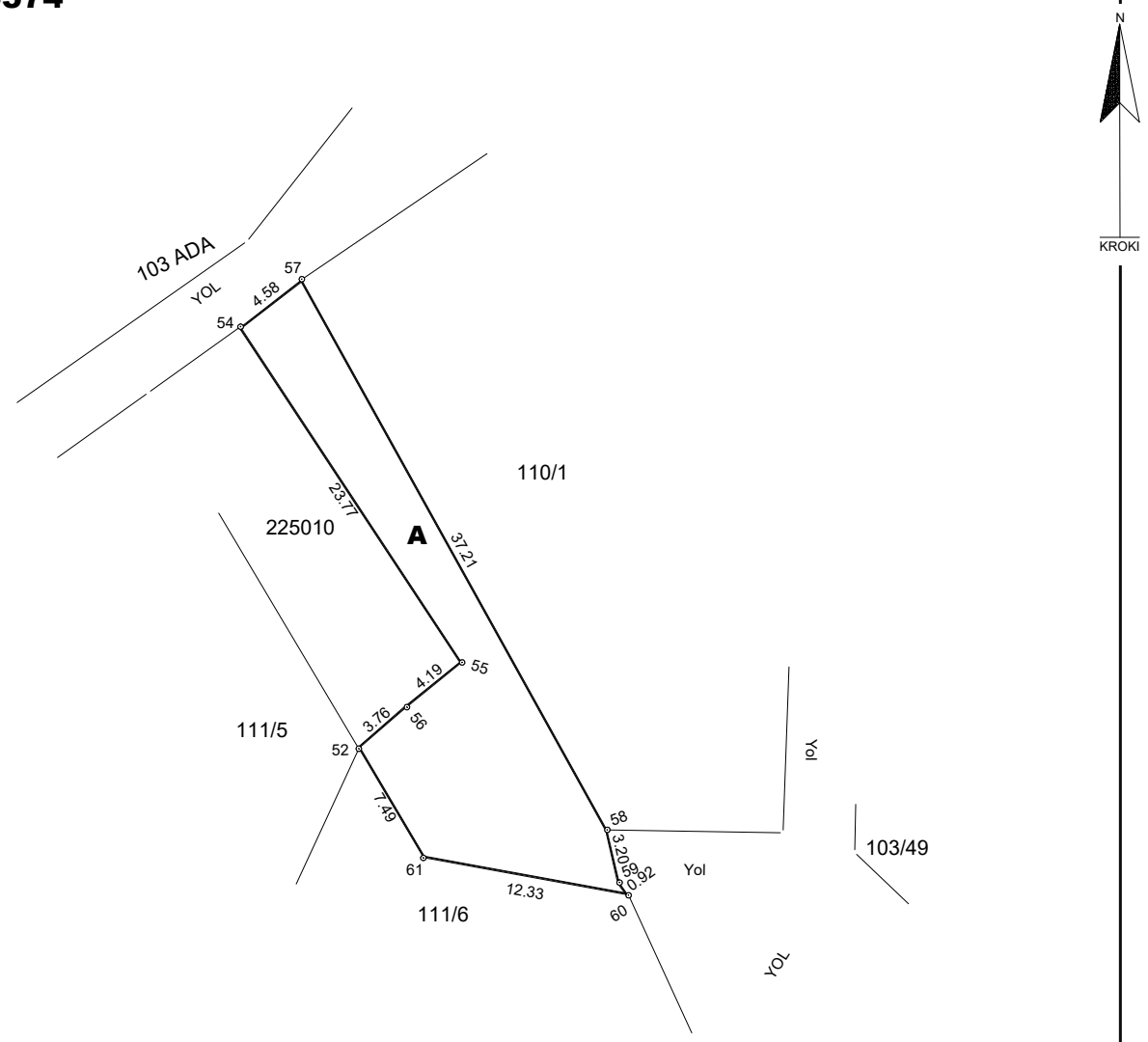

NN	MK	Y	X	NN	MK	Y	X
52		402584.44	4098722.60	54	0.09	402577.46	4098747.54
55	0.09	402590.54	4098727.70	56	0.09	402587.29	4098725.06
57		402581.07	4098750.34	58		402599.12	4098717.81
59	0.09	402599.85	4098714.69	60		402600.39	4098713.94
61		402588.26	4098716.15				

Ada/Parsel	Noktalar	Hesap Alan
A	52,54,55,56,57,58,59,60,61	216.48

Elipsoid	GRS80	
Datum	ITRF96	
Başlangıç Epoku	2005.00	
Projeksiyon	UTM (3)	
D.O.M.	36	

Tescil Bildirimi ön sayfasına (EK-11A) uygun düzenlenerek kontrol edilmiştir.

	Düzenleyen Kadastro Müdürlüğü / Lisanslı Büro	Kontrol Eden Kontrol Memuru / Kontrol Mühendisi
Adı Soyadı	Mahmut MELEMEN	Taha GÜRKAN
Tarih		
İmza		

EK-11A

Kadastro gören yerlerde yapılacak düzeltme ve değişiklik işlemleri için

TESCİL BİLDİRİMİ

İli	İlçesi	Mahalle veya Köyü	Mevkii
MERSİN	TARSUS	KAYADİBİ	-

~~Düzeltme - Ayırma - Yola Terk - Birleştirme - Cins Değişikliği -~~ İdari Yoldan Tescil

Kütük Sa.No.	Pafta No	Ada No	Parsel No	YÜZÖLÇÜMÜ Ha	m^2	dm^2	Cinsi	Maliki	Düşünceler ve İşlemin Şekli
	N33C24D1C	0	A	-	0130	96	HAM TOPRAK	MALİYE HAZİNESİ	İdari Yoldan Tescil. Satış, kiralama vb. işlemler öncesinde Kültür Varlıklarını Koruma Bölge Müdürlüğünden görüş sorulması gerekmektedir. İçme-Kullanma Suyu Havzalarının Korunmasına Dair Yönetmelik 12. Madde hükümlerine uyulması ve taşkına tedbir alınması şartı ile tescilinin yapılmasında DSİ sorumluluk sahası açısındanbir sakınca bulunmamaktadır.

ONAY
Kadastro Müdürü

Fen Kayıt Yıl/No	Düzenleyen Kadastro Müdürlüğü	Kontrol Eden		Fen Klasörüne ve MEGSİS'e		Belediye Encümeni
		Kontrol Memuru	Kontrol Mühendisi	İşlenmiştir	Kontrol edilmiştir	Tarih : No :
Adı Soyadı	Mahmut MELEMEN		Taha GÜRKAN			...../...../20..... Tarih ve ..... Yevmiye Numarası ile tescil edilmiştir.
Tarih						
İmza						

TDA No: 295575

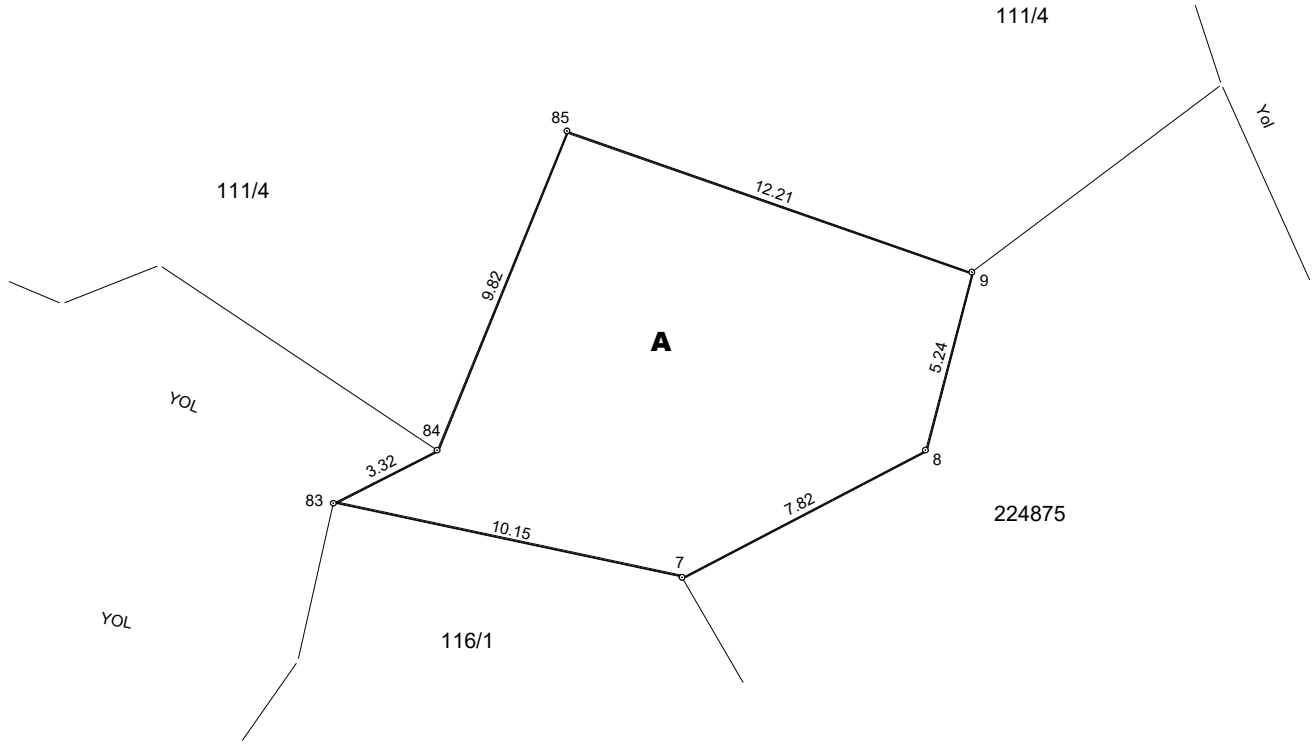

NN	MK	Y	X	NN	MK	Y	X
7		402666.16	4098620.16	8	0.09	402673.10	4098623.79
9		402674.42	4098628.86	83		402656.23	4098622.28
84		402659.19	4098623.79	85		402662.89	4098632.88

Ada/Parsel	Noktalar	Hesap Alan
A	7,8,9,83,84,85	130.96

Elipsoid	GRS80
Datum	ITRF96
Başlangıç Epoku	2005.00
Projeksiyon	UTM (3)
D.O.M.	36

Tescil Bildirimi ön sayfasına (EK-11A) uygun düzenlenerek kontrol edilmiştir.

	Düzenleyen Kadastro Müdürlüğü / Lisanslı Büro	Kontrol Eden Kontrol Memuru / Kontrol Mühendisi
Adı Soyadı	Mahmut MELEMEN	Taha GÜRKAN
Tarih		
İmza		

EK-11A

Kadastro gören yerlerde yapılacak düzeltme ve değişiklik işlemleri için

TESCİL BİLDİRİMİ

İli	İlçesi	Mahalle veya Köyü	Mevkii
MERSİN	TARSUS	KAYADİBİ	-

~~Düzeltme - Ayırma - Yola Terk - Birleştirme - Cins Değişikliği -~~ İdari Yoldan Tescil

Kütük Sa.No.	Pafta No	Ada No	Parsel No	YÜZÖLÇÜMÜ Ha	m^2	dm^2	Cinsi	Maliki	Düşünceler ve İşlemin Şekli
	N33C24D4A	0	A	-	0472	96	HAM TOPRAK	MALİYE HAZİNESİ	İdari Yoldan Tescil. Satış, kiralama vb. işlemler öncesinde Kültür Varlıklarını Koruma Bölge Müdürlüğünden görüş sorulması gerekmektedir. Krokisinde A harfi ile gösterilen yapı bulunmaktadır. İçme-Kullanma Suyu Havzalarının Korunmasına Dair Yönetmelik 10. Madde hükümlerine uyulması ve taşkına tedbir alınması şartı ile tescilinin yapılmasında DSİ sorumluluk sahası açısındanbir sakınca bulunmamaktadır.

ONAY
Kadastro Müdürü

Fen Kayıt Yıl/No	Düzenleyen Kadastro Müdürlüğü	Kontrol Eden		Fen Klasörüne ve MEGSİS'e		Belediye Encümeni
		Kontrol Memuru	Kontrol Mühendisi	İşlenmiştir	Kontrol edilmiştir	Tarih : No :
Adı Soyadı	Mahmut MELEMEN		Taha GÜRKAN			...../...../20..... Tarih ve ..... Yevmiye Numarası ile tescil edilmiştir.
Tarih						
İmza						

TDA No: 295576

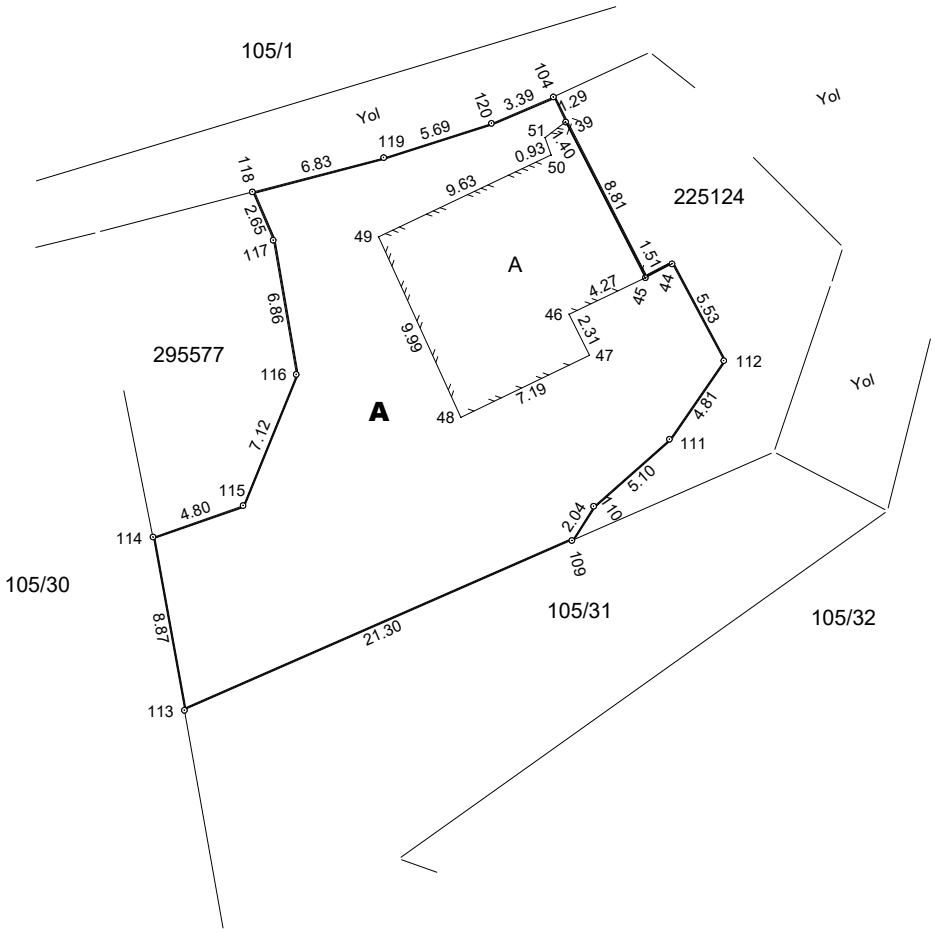

NN	MK	Y	X	NN	MK	Y	X
39	0.09	402224.20	4098333.41	44	0.09	402229.56	4098326.27
45	0.09	402228.22	4098325.57	46	0.09	402224.37	4098323.73
47	0.09	402225.41	4098321.66	48	0.09	402218.93	4098318.55
49	0.09	402214.78	4098327.63	50	0.09	402223.48	4098331.76
51	0.09	402223.17	4098332.63	104	0.09	402223.58	4098334.68
109		402224.51	4098312.34	110	0.09	402225.61	4098314.06
111	0.09	402229.43	4098317.44	112	0.09	402232.16	4098321.40
113		402205.00	4098303.79	114		402203.42	4098312.52
115	0.09	402207.96	4098314.10	116	0.09	402210.64	4098320.70
117	0.09	402209.48	4098327.46	118	0.09	402208.43	4098329.90
119	0.09	402215.04	4098331.62	120	0.09	402220.47	4098333.35

Ada/Parsel	Noktalar	Hesap Alan
A	104,109,110,111,112,113,114,115,116,117,118 119,120	472.96

Elipsoid	GRS80	
Datum	ITRF96	
Başlangıç Epoku	2005.00	
Projeksiyon	UTM (3)	
D.O.M.	36	

Tescil Bildirimi ön sayfasına (EK-11A) uygun düzenlenerek kontrol edilmiştir.

	Düzenleyen Kadastro Müdürlüğü / Lisanslı Büro	Kontrol Eden Kontrol Memuru / Kontrol Mühendisi
Adı Soyadı	Mahmut MELEMEN	Taha GÜRKAN
Tarih		
İmza		

EK-11A

Kadastro gören yerlerde yapılacak düzeltme ve değişiklik işlemleri için

TESCİL BİLDİRİMİ

İli	İlçesi	Mahalle veya Köyü	Mevkii
MERSİN	TARSUS	KAYADİBİ	-

~~Düzeltme - Ayırma - Yola Terk - Birleştirme - Cins Değişikliği -~~ İdari Yoldan Tescil

Kütük Sa.No.	Pafta No	Ada No	Parsel No	YÜZÖLÇÜMÜ Ha^2	m^2	dm^2	Cinsi	Maliki	Düşünceler ve İşlemin Şekli
	N33C24D4A	0	A	-	0119	73	HAM TOPRAK	MALİYE HAZİNESİ	İdari Yoldan Tescil. Satış, kiralama vb. işlemler öncesinde Kültür Varlıklarını Koruma Bölge Müdürlüğünden görüş sorulması gerekmektedir. İçme-Kullanma Suyu Havzalarının Korunmasına Dair Yönetmelik 10. Madde hükümlerine uyulması ve taşkına tedbir alınması şartı ile tescilinin yapılmasında DSİ sorumluluk sahası açısındanbir sakınca bulunmamaktadır.

ONAY
Kadastro Müdürü

Fen Kayıt Yıl/No	Düzenleyen Kadastro Müdürlüğü	Kontrol Eden		Fen Klasörüne ve MEGSİS'e		Belediye Encümeni
		Kontrol Memuru	Kontrol Mühendisi	İşlenmiştir	Kontrol edilmiştir	Tarih : No :
Adı Soyadı	Mahmut MELEMEN		Taha GÜRKAN			...../...../20..... Tarih ve ..... Yevmiye Numarası ile tescil edilmiştir.
Tarih						
İmza						

TDA No: 295577

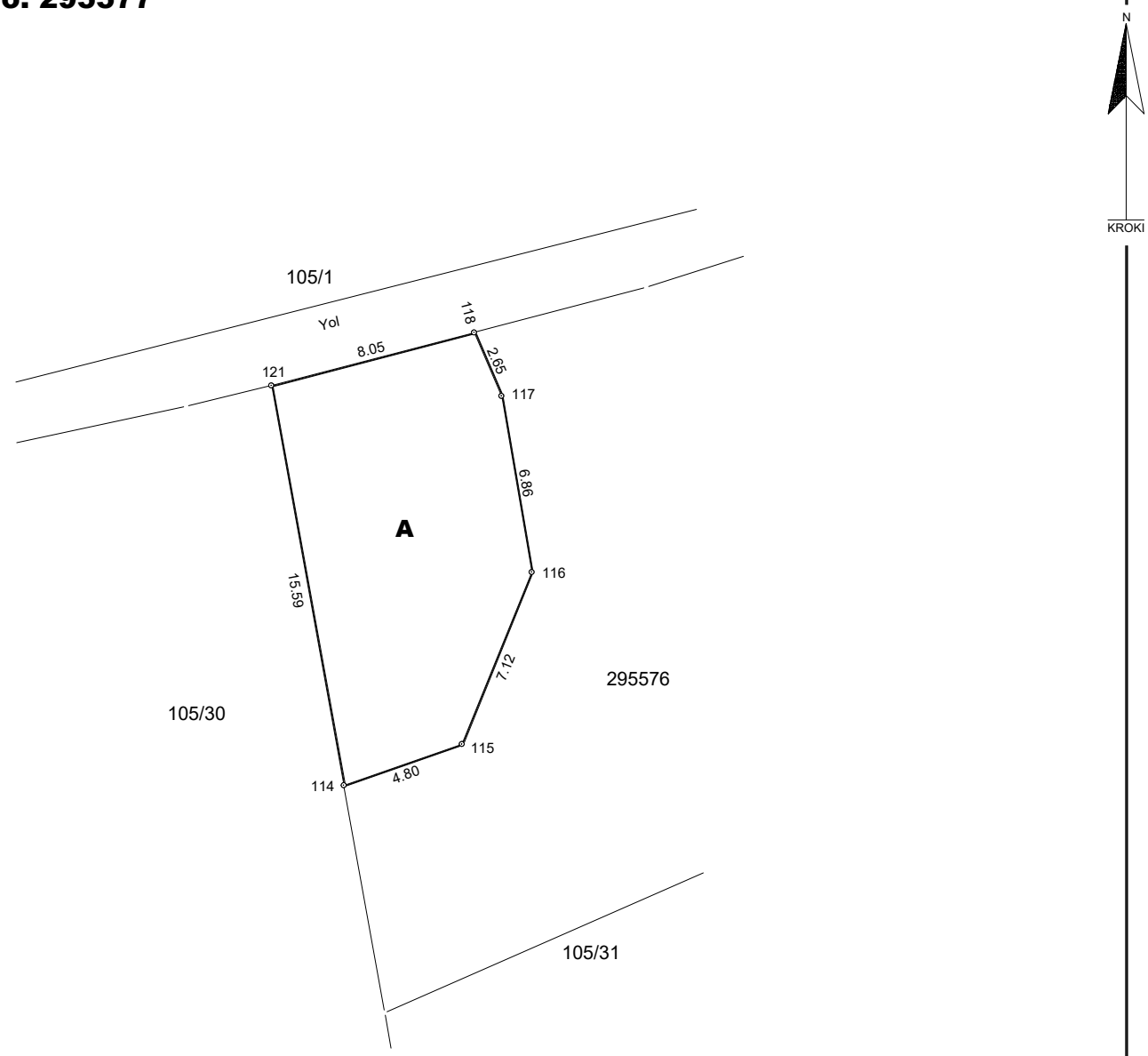

NN	MK	Y	X	NN	MK	Y	X
114		402203.42	4098312.52	115	0.09	402207.96	4098314.10
116	0.09	402210.64	4098320.70	117	0.09	402209.48	4098327.46
118	0.09	402208.43	4098329.90	121		402200.64	4098327.86

Ada/Parsel	Noktalar	Hesap Alan
A	114,115,116,117,118,121	119.73

Elipsoid	GRS80
Datum	ITRF96
Başlangıç Epoku	2005.00
Projeksiyon	UTM (3)
D.O.M.	36

Tescil Bildirimi ön sayfasına (EK-11A) uygun düzenlenerek kontrol edilmiştir.

	Düzenleyen Kadastro Müdürlüğü / Lisanslı Büro	Kontrol Eden Kontrol Memuru / Kontrol Mühendisi
Adı Soyadı	Mahmut MELEMEN	Taha GÜRKAN
Tarih		
İmza		